10.

Cotobade - Campo Lameiro

Diseño©Sesa Silva

Etapa 11.: VMLG.10. Cotobade (A Chan) - Sacos - Campo Lameiro

VMLG.10

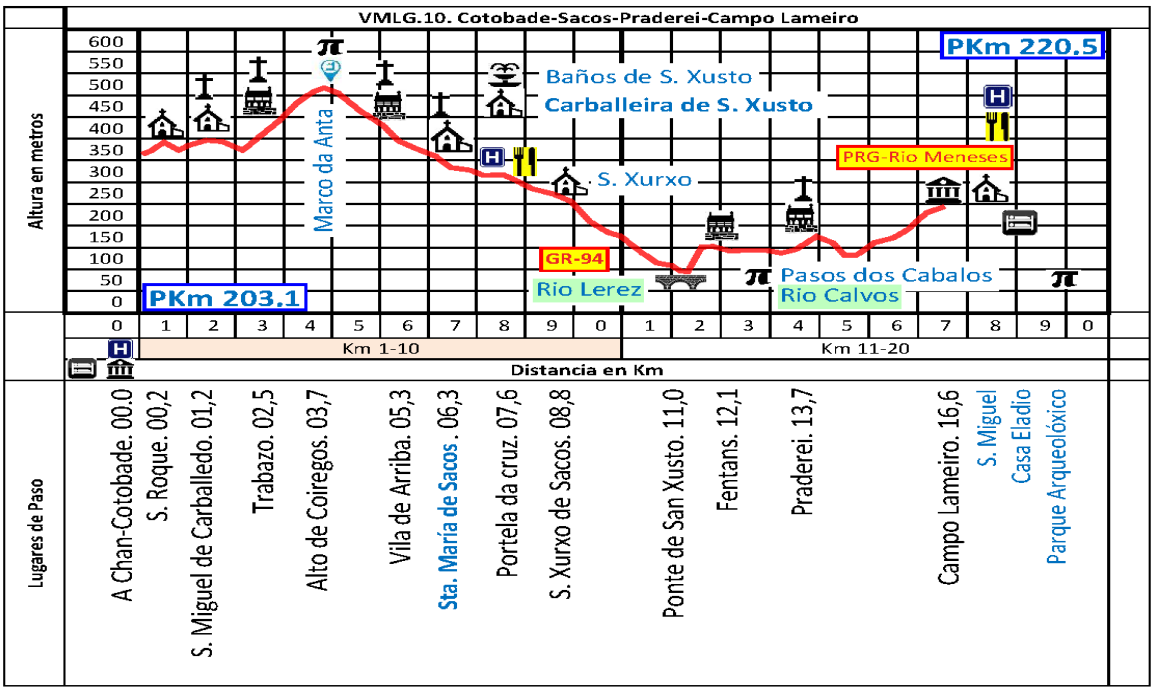

GoogleMaps.10

Distancia 17,32 km. Desnivel positivo 494 m

Variante Praderrei. Paso dos Cavalos

TRACK

WL.10

ITINERARIOS

AllTrails.10

DESCRIPCION. Playa Fluvial de Carballedo. *INFO* Chan-Carballedo: Estanco Cuiñas +34 652834140

Albergue de A Chan - Cotobade (Km 0,00). Pasando por el núcleo urbano de A Chan

San Roque (Km 0,3). **Igrexa S. Miguel de Carballedo (1,3)**
Saliendo a izquierda por la parte posterior de la iglesia. Camino asfaltado. **Pontillón de Trabazo**

Trabazo (2,3). **Alto de Coiregos. Fonte** (3,8). **Cruceiro do Agro**. **Vila de Arriba (Km 5,4)**

Santa María de Sacos (Km 6,3) Vila de Abaixo. El camino que conduce a la Estrada Vella, suele estar cerrado por la maleza (**Linea Verde**). Usar acceso por carretera general Pontevedra Ourense N-541. Tráfico intenso. Cruce peligroso de N-541 pasada la Granja Agricola. Estrada Vella. Paso bajo la N-541, ESTACIÓN ARQUEOLÓXICA DO OUTEIRO (Km 7,3). ***Opcion por PRG-29,Carballeira y Baños de San Xusto***

Un camino vecinal paralelo a la N-541 conduce a la **Estación Arqueoloxica de A Portela da Cruz**.
Pazo Bermúdez de Castro (Km 8,5). (N-541). **(8,9) San Xurxo de Sacos**.
Opcion por GR-94-Rural de Galicia si estuviera limpio.

Ponte de San Xusto o Ponte Nova **(Km 11,0) Rio Lerez**. Camino calzado. **Fentáns. Km 12,3**.
Cra. de Campo Lameiro PO-230. **Desvio a Praderrei (14,1)**.
Desvío opcional a Praderrei por el Paso dos Cavalos (Rio Calvos). No recomendado en tiempo de lluvia.
Cruceiro de Praderrei (14,7). Acceso al **Pontillón del Rio Maneses** (14,5) **PR-G 230 Senda do río Maneses**
Rego de Maneses y Pontillón dos Manés. Centro de Salud. **CONCELLO DE CAMPO LAMEIRO (A Lagoa).**

ALBERGUES Asociados. Campo Lameiro. INFO: Casa Argibay. Eladio. Tel. 0034617214001

WL.10

PATRIMONIO

Pdf.10

https://campolameiro.org/es/patrimonio-historico/
Patrimonio Histórico
https://campolameiro.org/es/patrimonio-historico/#
Centro de Interpretación
http://www.paar.es/?lang=gl
Patrimonio Natural
https://campolameiro.org/es/patrimonio-natural/

VMLG.10. Cotobade-Campo Lameiro

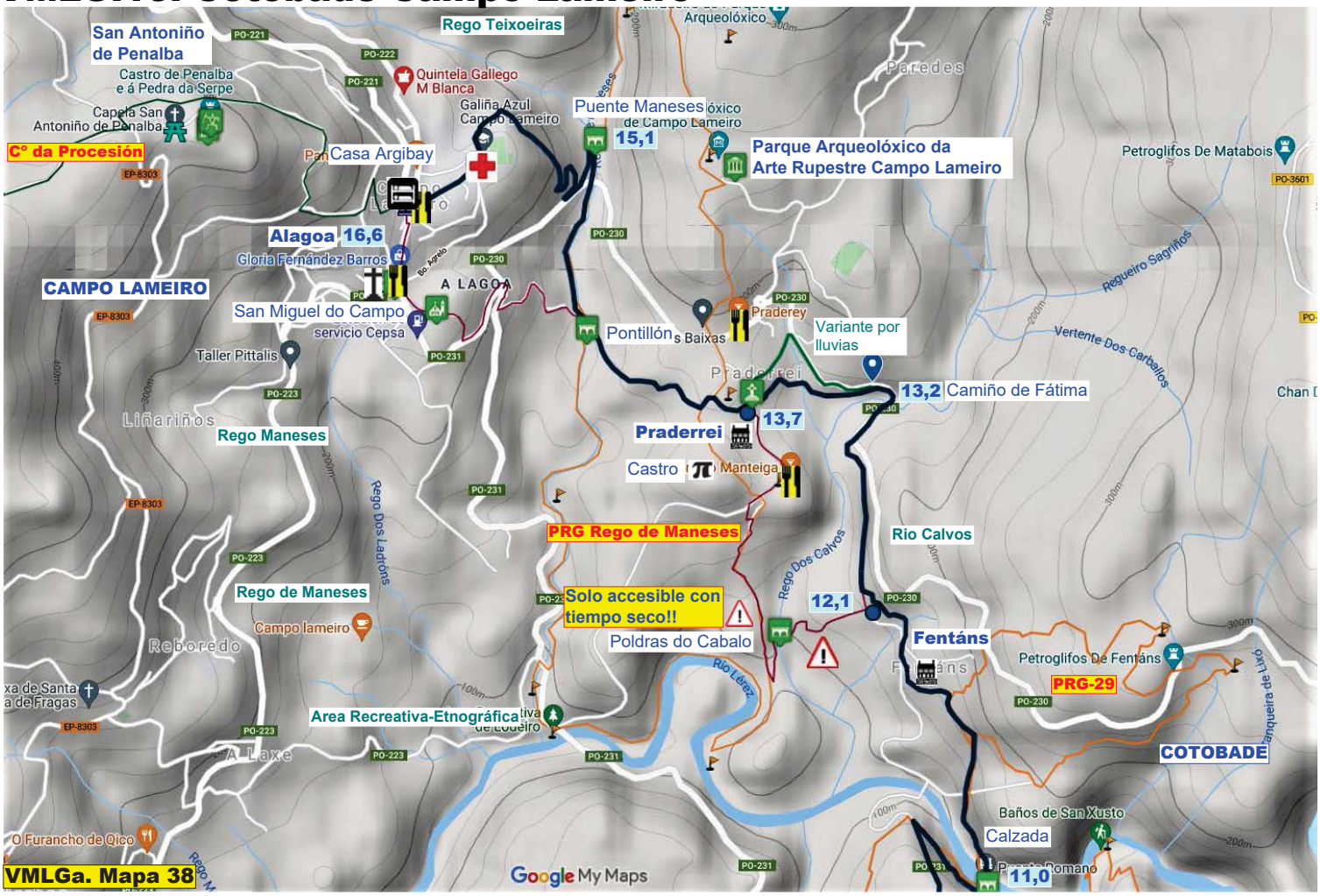

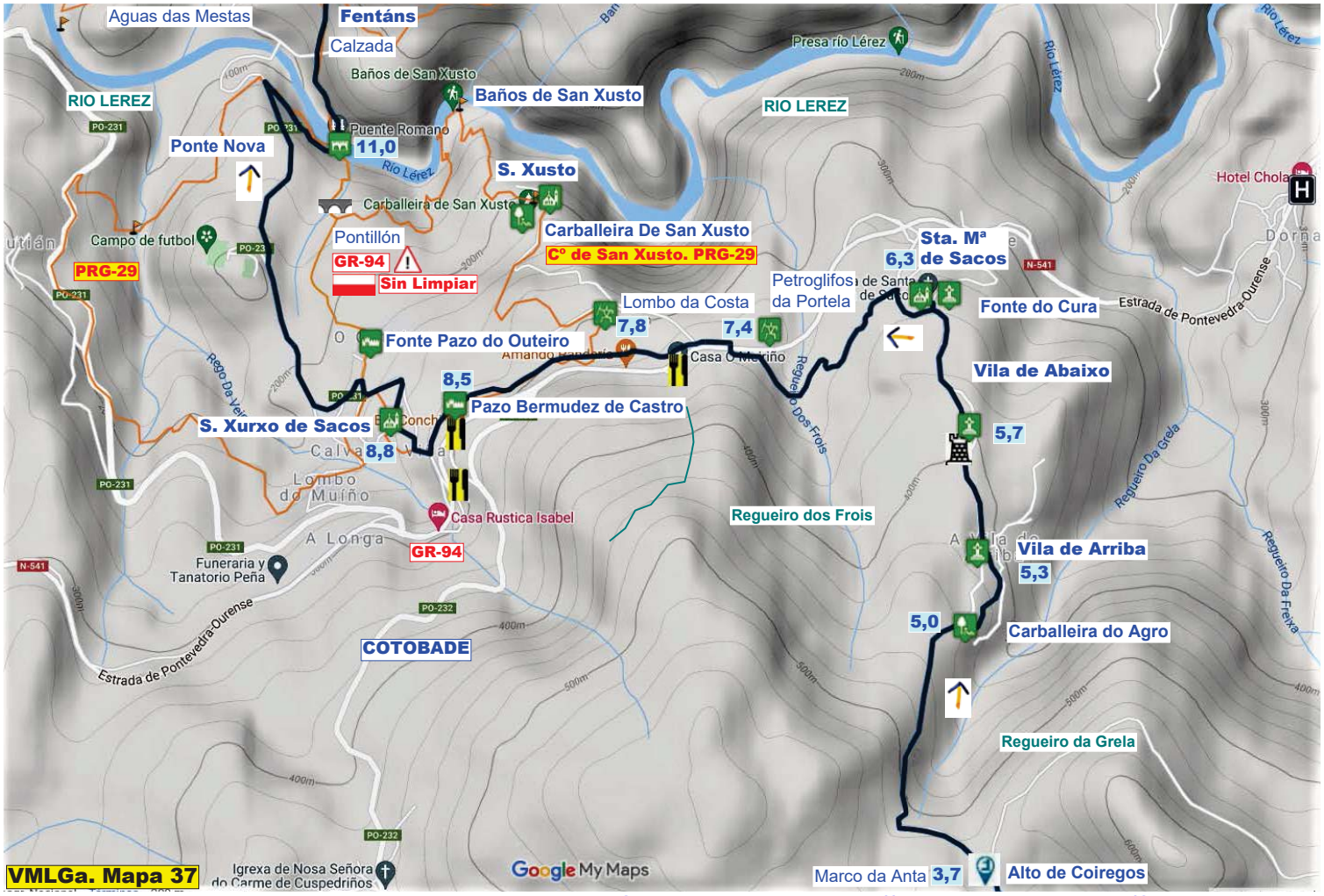

© Luis do Freixo http://www.caminador.es/?page_id=117

VMLG.10. Cotobade-Campo Lameiro

Marco da Anta
https://www.galiciamaxica.eu/galicia/marco_da_anta/

3,7 Alto de Coiregos

Monte Coirego

Observatorio Astronómico de...
Cerrado temporalmente

Trabazo

2,5

Pontella

Cuspedriños

casa de vacaciones

Paraños

Carballedo

1,2

S Miguel de Carballedo

Cruz do Castro

Foxo

COTOBADE

Parque Publico Infantil De Carballedo

San Roque

0,2

Sión

Plaia fluvial de Carballedo

0,0

Rio Almofrei

Rego de Chan das Latas

A Braña Doade

O Batán

VMLGa. Mapa 36

© Luis do Freixo http://www.caminador.es/?page_id=117