VMLG.14a
Teo-Brión-Negreira

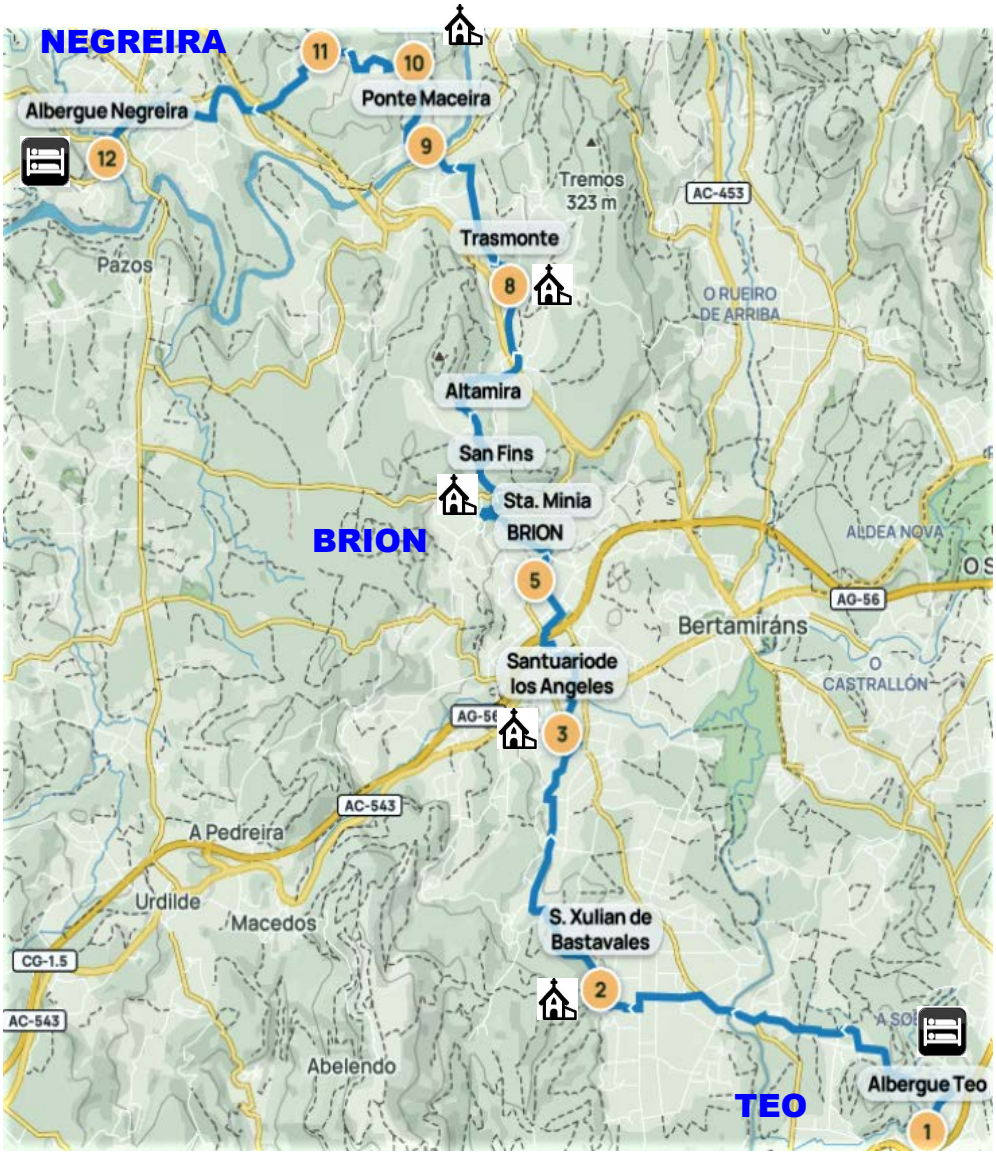

AUTOR: Luis do Freixo
Deseño Gráfico Sesasilva

ITINERARIO
VMLG.14a

Diseño©Sesa Silva

Etapa 15.: VMLG.14a. Teo - Brión - Negreira

VMLG.14a/b

Guia pdf 14a

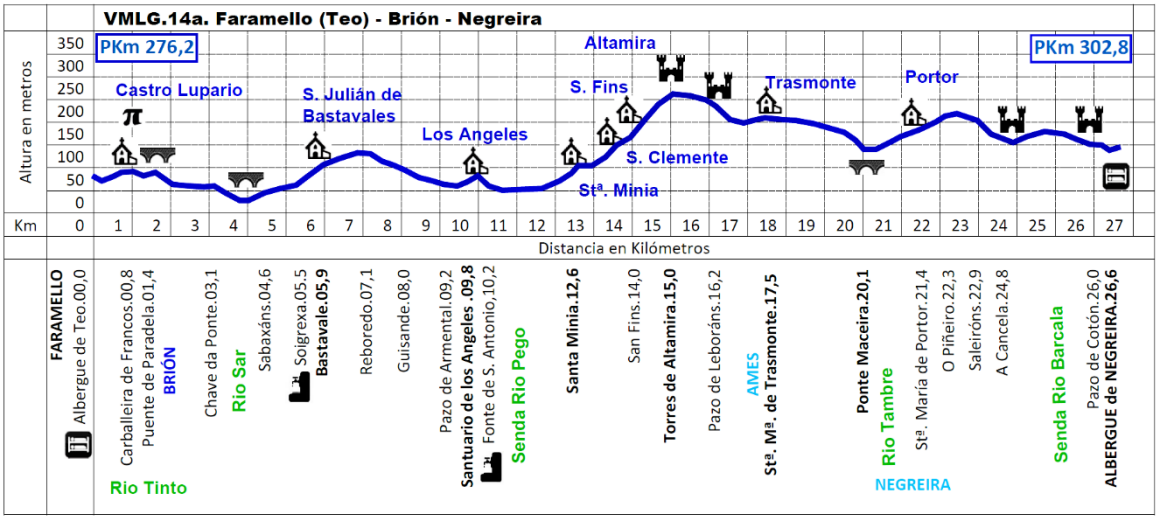

ITINERARIOS

TRACK	AllTrails.14a	WL. 14a	G.Maps 14

Desde el **Albergue de Teo(Km 0,0),** nos dirigimos a Rua de Francos y pasada la **Capela de S. Martiño** **(Km0,8)** abandonamos el Camino Portugués a través de la **Carballeira de Francos** para dirigirnos al **Ponte da Paradela (1,4)**,

Sin Señalizar. **CONCELLO de BRIÓN** Por pequeños caminos rurales: **Castro Lupario**, Xinzo, **Chave da Ponte (4,0)**, Rio Sar. **Sabaxáns (Km 4,6). Soigrexa (5,5). San Xulián de Bastavales (5,9)**

Lugares de **Vilas**, **Reboredo**, **Guisande y Sanín (Km 8,6). Pazo de Armental (9,2). Av. dos Anxeles (AC-300**).

Servicios de restauración y Hostelería. **Santuario de Nosa Señora dos Anxeles (Km 9,8)**

Camiño da Fonte (camino de Santiago). **Fontes de S. Antonio y Alqueidón (10,2)** Rua da Pomba. **Senda do Rio Pego**
Senderismo de Brión. Av. dos Anxeles. Rotonda AG-56. R/ Tarrio (Km 11,5). R/ Pedrouzos. **Centro de Salud**.
R/ Pedriñas. Av de Sta. Minia. **Carballeira y Santuario de Sta. Minia (Km 12,6)**

Virando a izquiera para eludir la Cra. AC-451, seguimos a **Cabreiros, Quintáns y Guldrís** (Km 12,6).
Si el estado del Camino lo permite, por Cruz do Adro y **Capela de S. Clemente** llegamos a **S. Fins de Brión (Km 14,0)**
De no ser posble, usar una carretera local a la izquierda por el lugar de Guldrís.

Por Roteiros de la **Batalla de Altamira** seguimos a las **Torres de Altamira (15,0)**

CONCELLO de AMES. Pazo de Leboráns (16,2), Cruce peligroso de la AC-544 en **Portanxil**.
Stª Mª de Trasmonte (Km 17,5). Encuentro con **VMLG.14b** y **Camino Xacobeo a Fisterra y Muxía**.
Ponte Maceira (Km 20,1) .

CONCELLO de NEGREIRA. La Vía Mariana se desvía del **Camino de Fisterra** por **Stª Mª de Portor (21,4), Piñeiro** y **Saleiróns,** para encontrarlo de nuevo en el **Pazo de Albariña**, lugar de **A Chancela** (Km 24,9). **Pazo de Cotón (Km 26,0)**

Albergue Municipal de Negreira (Pk. 26,6)

Albergue de Teo. https://caminodesantiago.consumer.es/albergue/albergue-de-peregrinos-de-teo
Albergue de Negreira https://www.caminodesantiago.gal/pt/recurso/280380571/albergue-de-peregrinos-de-negreira

WL.14a

PATRIMONIO

Pdf.14a

Patrimonio 14b

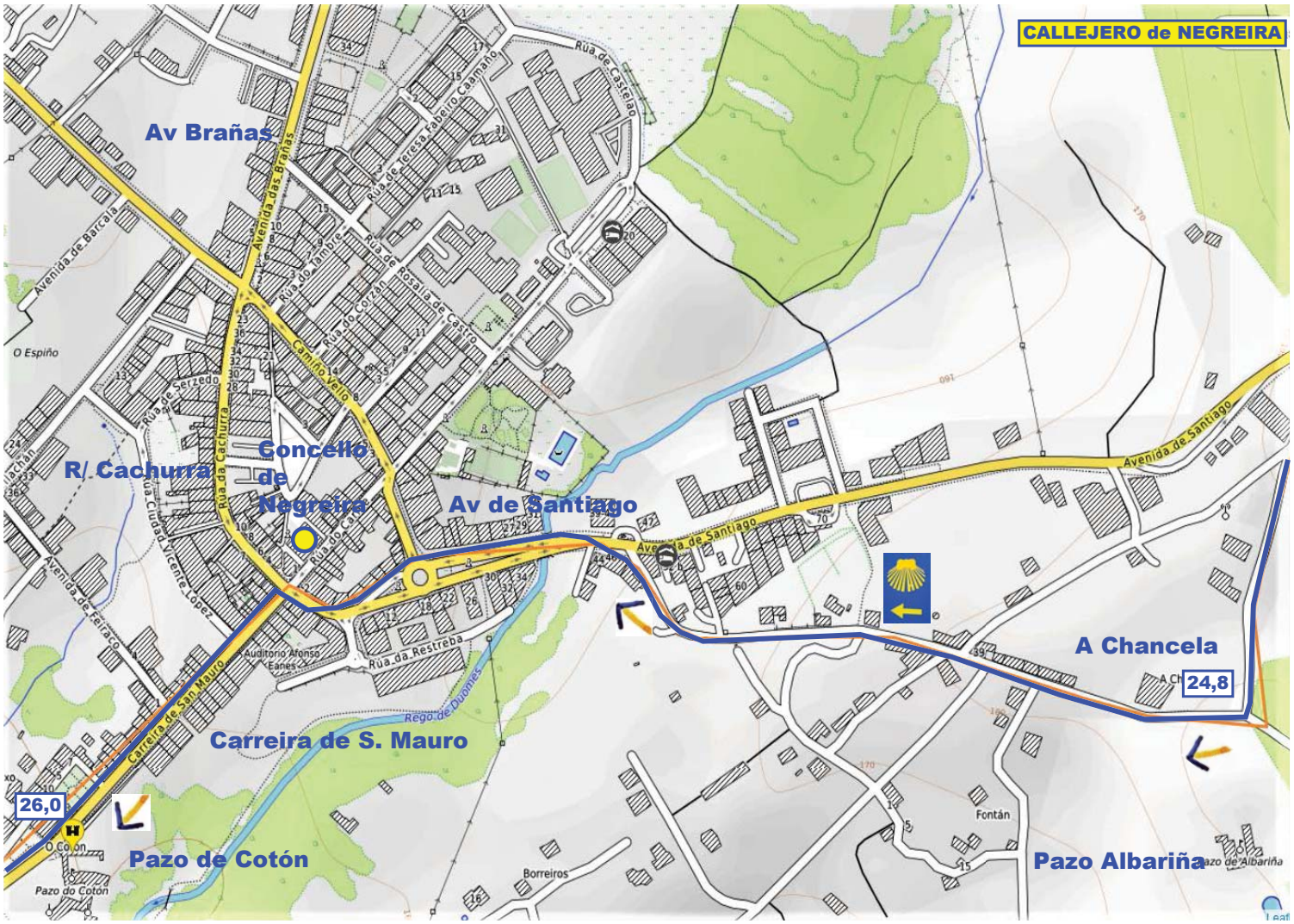
CALLEJERO de NEGREIRA
Av Brañas
R/ Cachurra
Concello de Negreira
Av de Santiago
A Chancela
24,8
Carreira de S. Mauro
26,0
Pazo de Cotón
Pazo Albariña

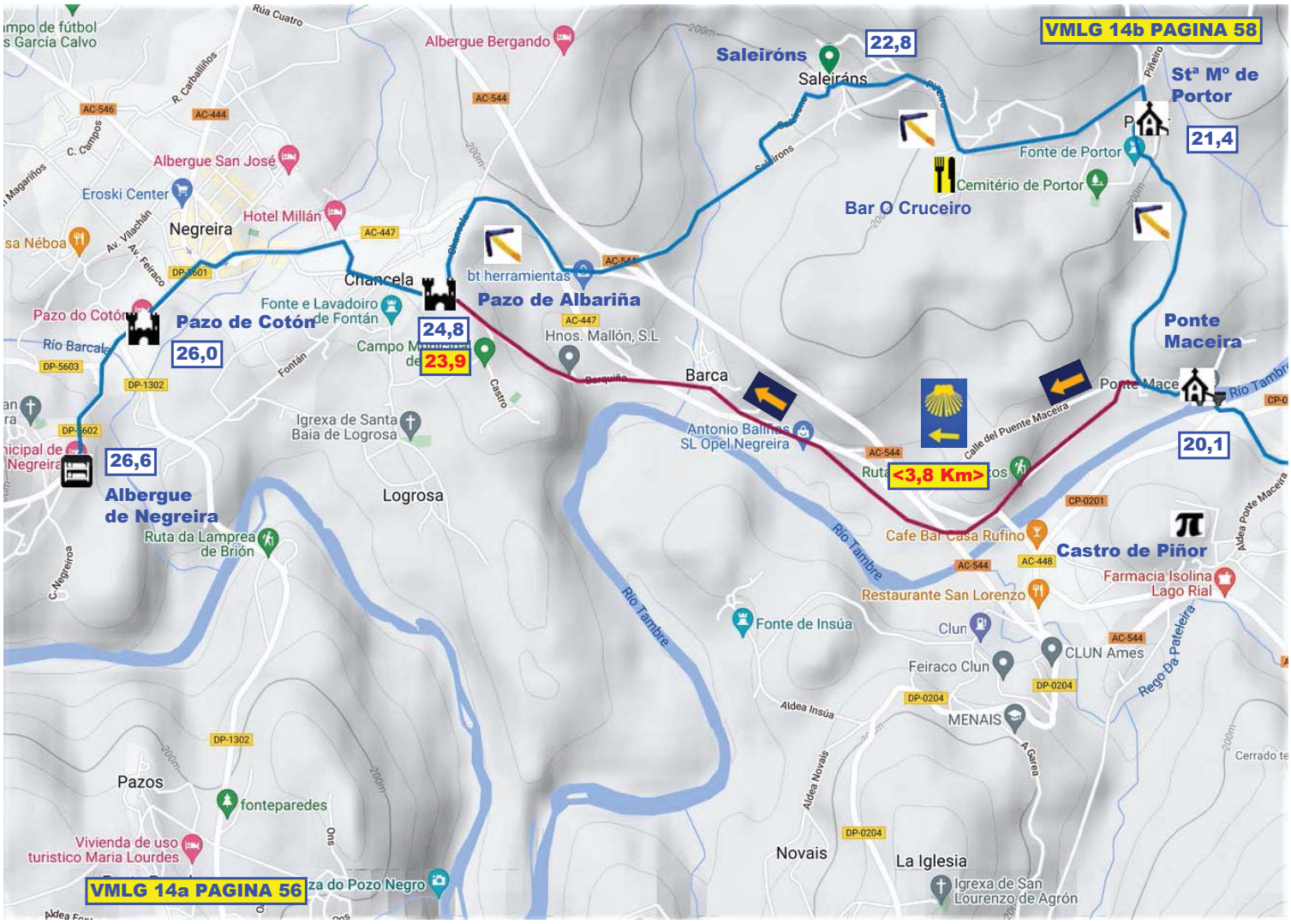
VMLG 14b PAGINA 58
Saleiróns
22,8
Stª Mº de Portor
21,4
Bar O Cruceiro
Pazo de Albariña
24,8
Pazo de Cotón
26,0
23,9
Ponte Maceira
20,1
Albergue de Negreira
26,6
<3,8 Km>
Castro de Piñor
VMLG 14a PAGINA 56

VMLG 14a. Teo -Brión - Negreira

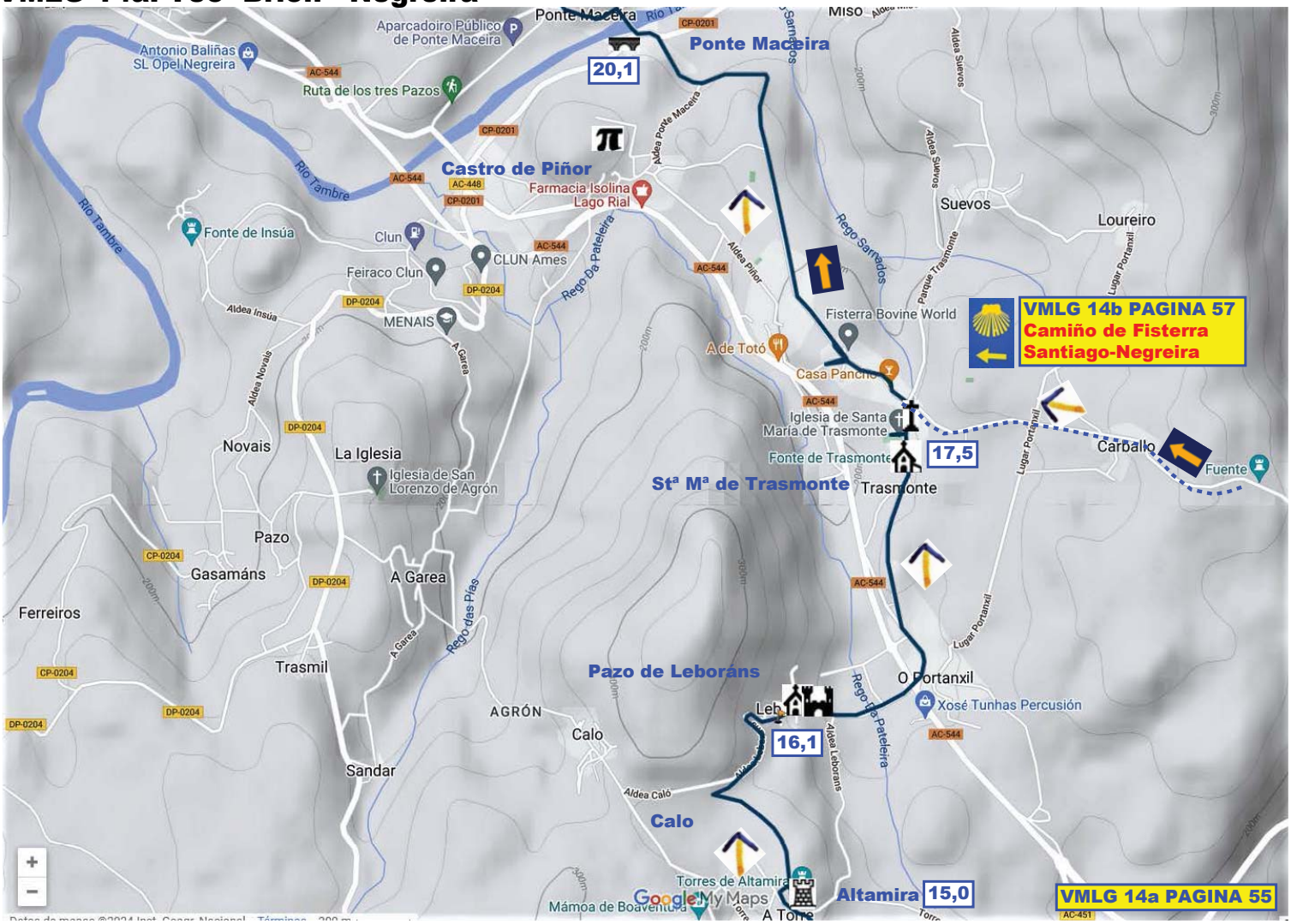

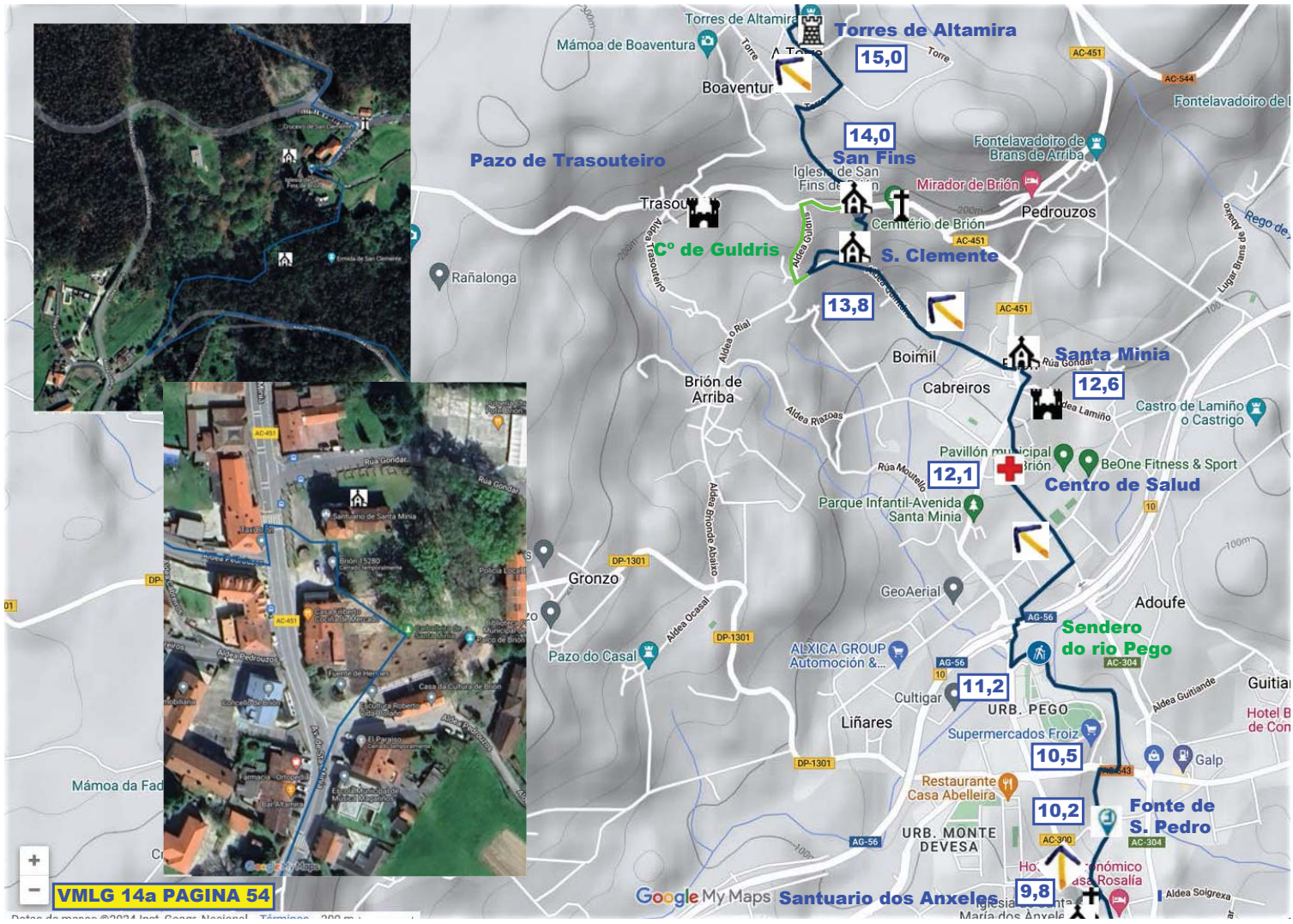

© Luis do Freixo http://www.caminador.es/?page_id=117

VMLG 14a. Teo -Brión - Negreira

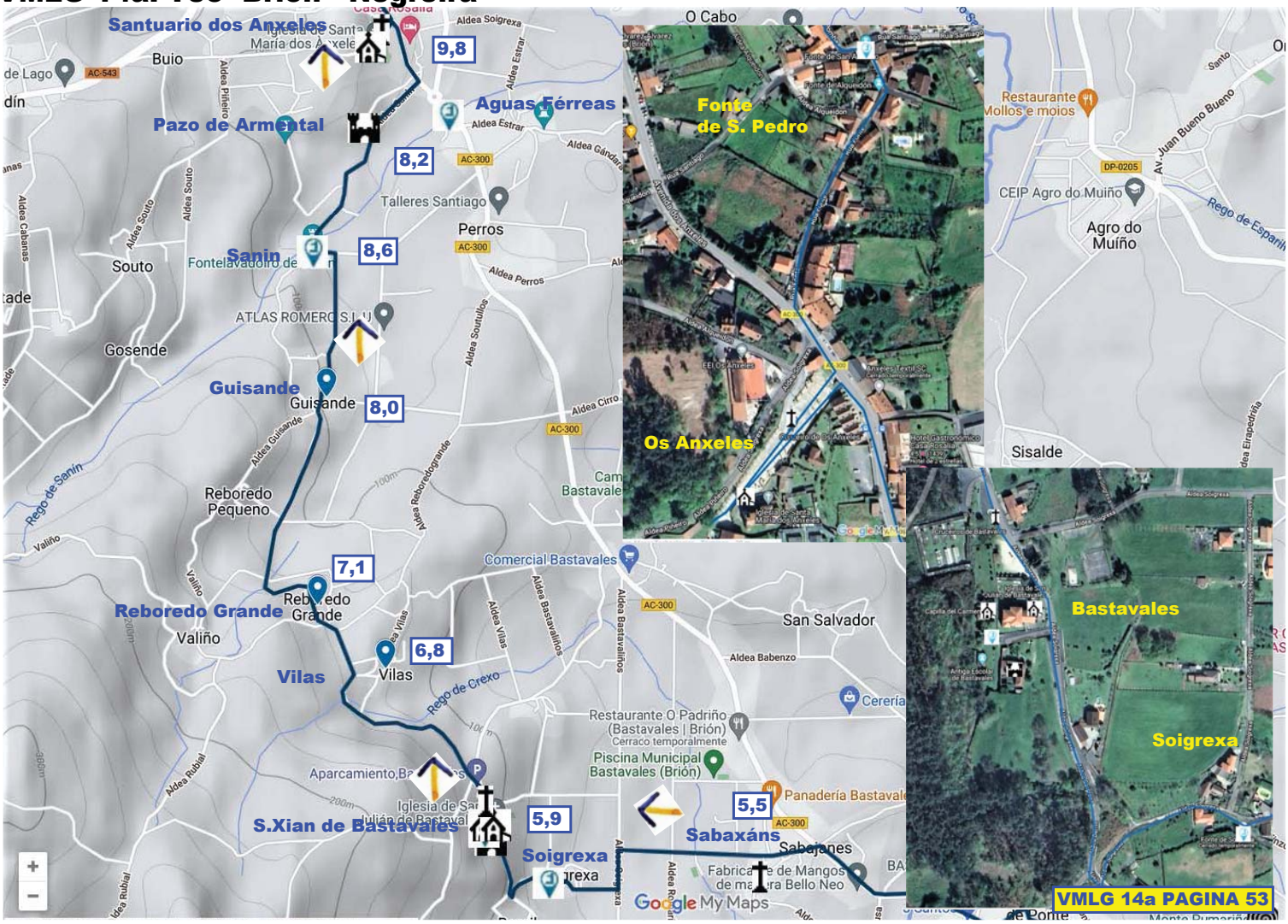

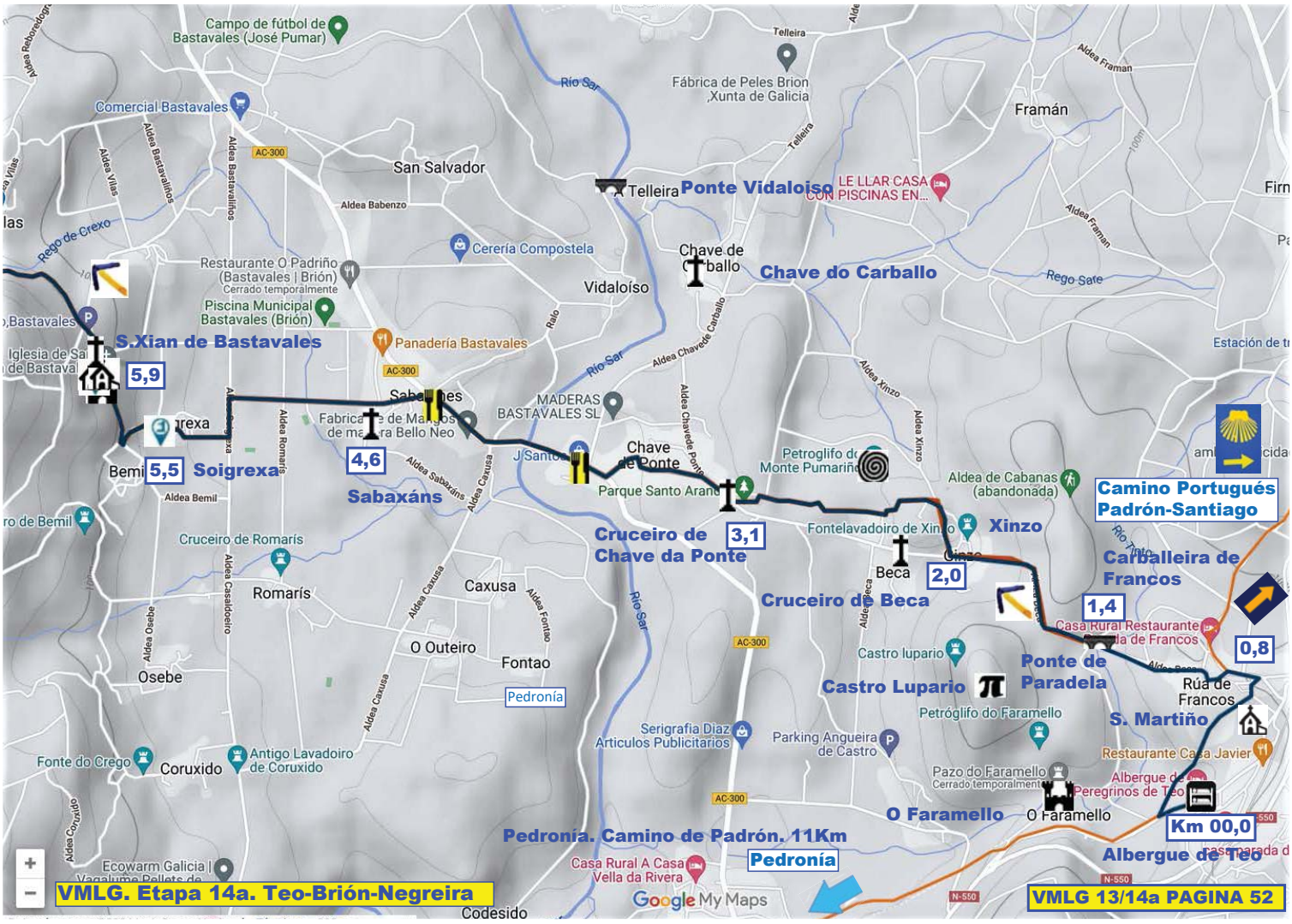

© Luis do Freixo http://www.caminador.es/?page_id=117

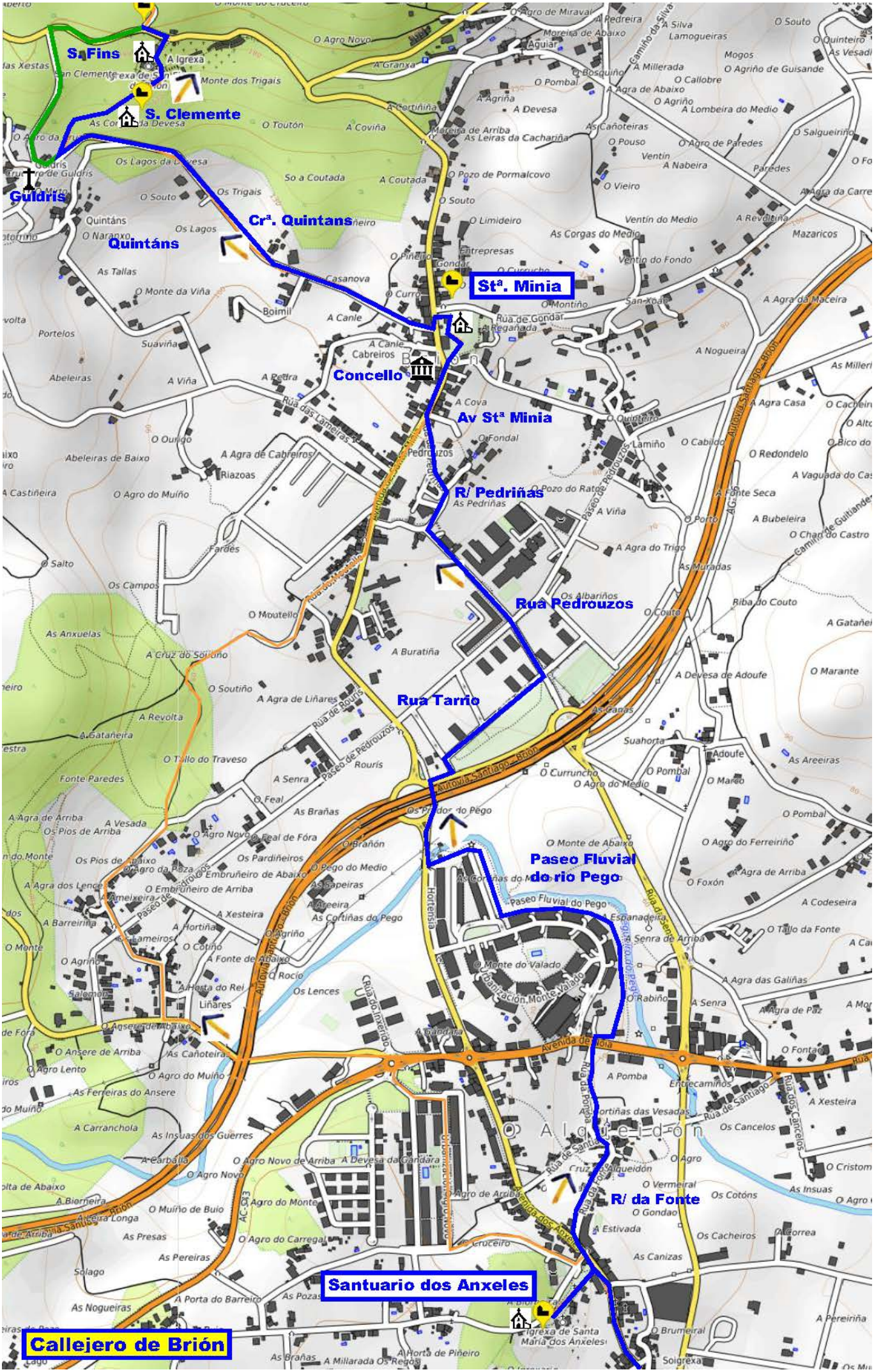

© Luis do Freixo http://www.caminador.es/?page_id=117