15.

A Baña-Negreira Sta. Comba-Mazaricos-Zás

AUTOR: Luis do Freixo
Deseño Gráfico: Sesa Silva

Diseño©Sesa Silva

Etapa 16.: VMLG.15. Negreira - A Baña - Stª. Comba - Zás

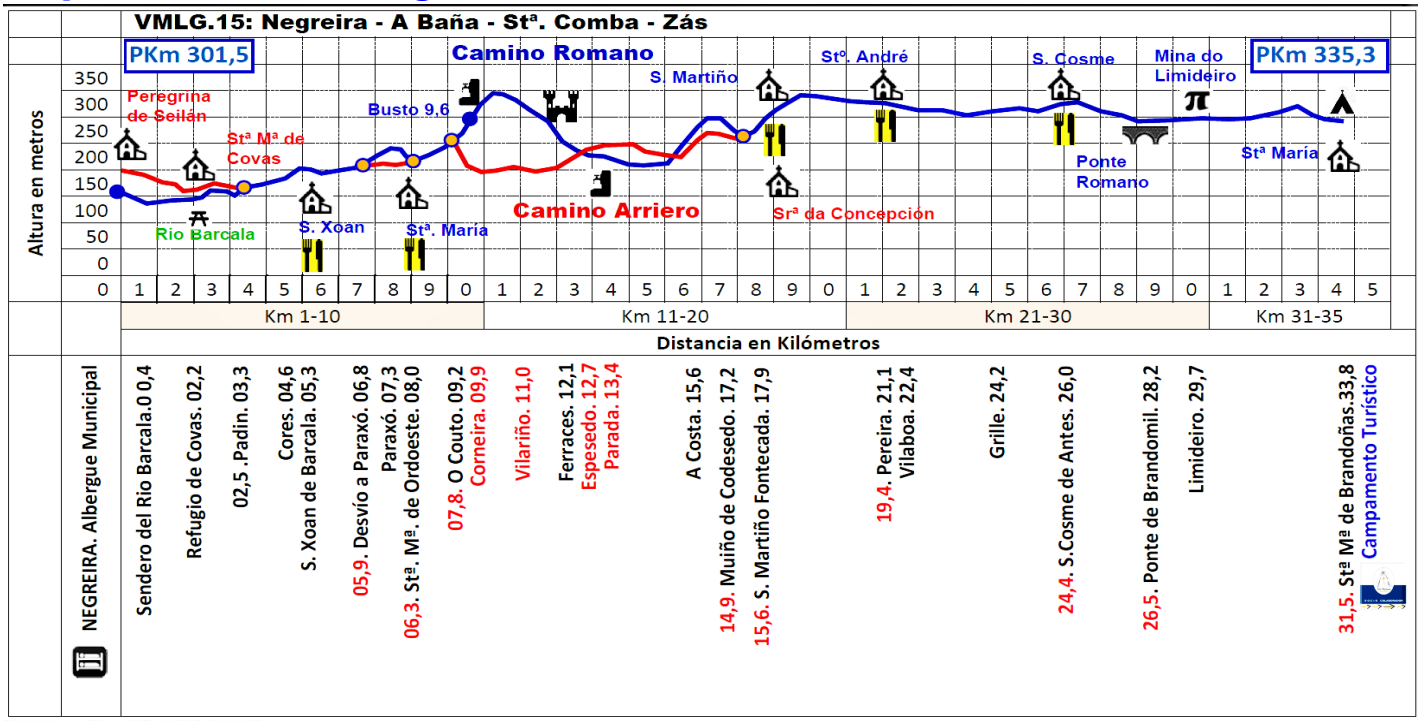

VMLG.15

ITINERARIOS- Track

WL. 15 | Camino Arriero 15 | AllTrails 15 | G.Maps 15

Sin Señalizar El Itinerario de Via Mariana pretende en éste tramo adaptarse al Itinerario del **"Camino a Muxía por Brandomil"**, desde la Capilla de la **Virgen Peregrina de Seilán** en A Baña. Por falta de alojamiento y mantenimiento de los caminos, se ha optado por un itinerario mejor adaptado a los caminantes combinado con el **"Camino Arriero"**.

CONCELLO de NEGREIRA

Desde el **Albergue Municipal de Negreira** por el **Sendero del Rio Barcala**, o desde la **Peregrina de Seilán**, ambos caminos confluyen entorno a la Iglesia de **Stª Mª. de Covas**, lugar de **Padín (PKm 3,3/2,5)**

CONCELLO de A BAÑA. Continúan juntos por Moldes, Cores y Seoane hasta **S. Xoan de Barcala (5,3/4,5)**.

***En el Km 6,8 el Camino Romano de Brandomil se desvía al lugar de Paraxó para coincidir de nuevo en Stª Mª de Ordoeste* (Pkm 8,0/6,3).**

Desde aqui el **Camino Romano** sube hasta los 350m por **Busto** y **Ferraces** mientras el **C. Arriero** llanea por **Corneira**, donde se habilita un futuro centro de Acogida de Peregrinos, **Vilariño y Espesedo,**

CONCELLO de Stª COMBA. **Parada.** De nuevo coinciden en el **Muiño de Codesedo** (Pkm 17,2/14,9) para continuar a **S. Martiño de Fontecada (17,9/15,6). y Stº. André de Pereira (21,1/19,4),**

CONCELLO de MAZARICOS Grille y **San Cosme de Antes** (26,0/24,4).

CONCELLO de ZÁS. Acalabanda, **Ponte Romano de Brandomil (Pk 28,2/26,5). Circuito de la Ciudad Romana. Limideiro (29,7) Mina Romana do Limideiro (Pkm 30,0/28,0)**

En tiempo seco el nivel del Embalse permite atajar hasta Brandoñas-A Gris(2,4Km)

Stª María de Brandoñas (Pk 33,8/31,5/32,4/30,4). Campamento Turistico Brandoñas

Albergue de Negreira https://www.caminodesantiago.gal/pt/recurso/280380571/albergue-de-peregrinos-de-negreira
Campamento Turístico de Brandoñas. A Gris, Zás **+34 981 19 12 83.** https://maps.app.goo.gl/sRkgeY2D8SvefF8MA

WL.15

PATRIMONIO

Pdf.15

Ciudad Romana de Brandomil

VMLG.15: Negreira-A Baña-Stª Comba-Mazaricos-Zás

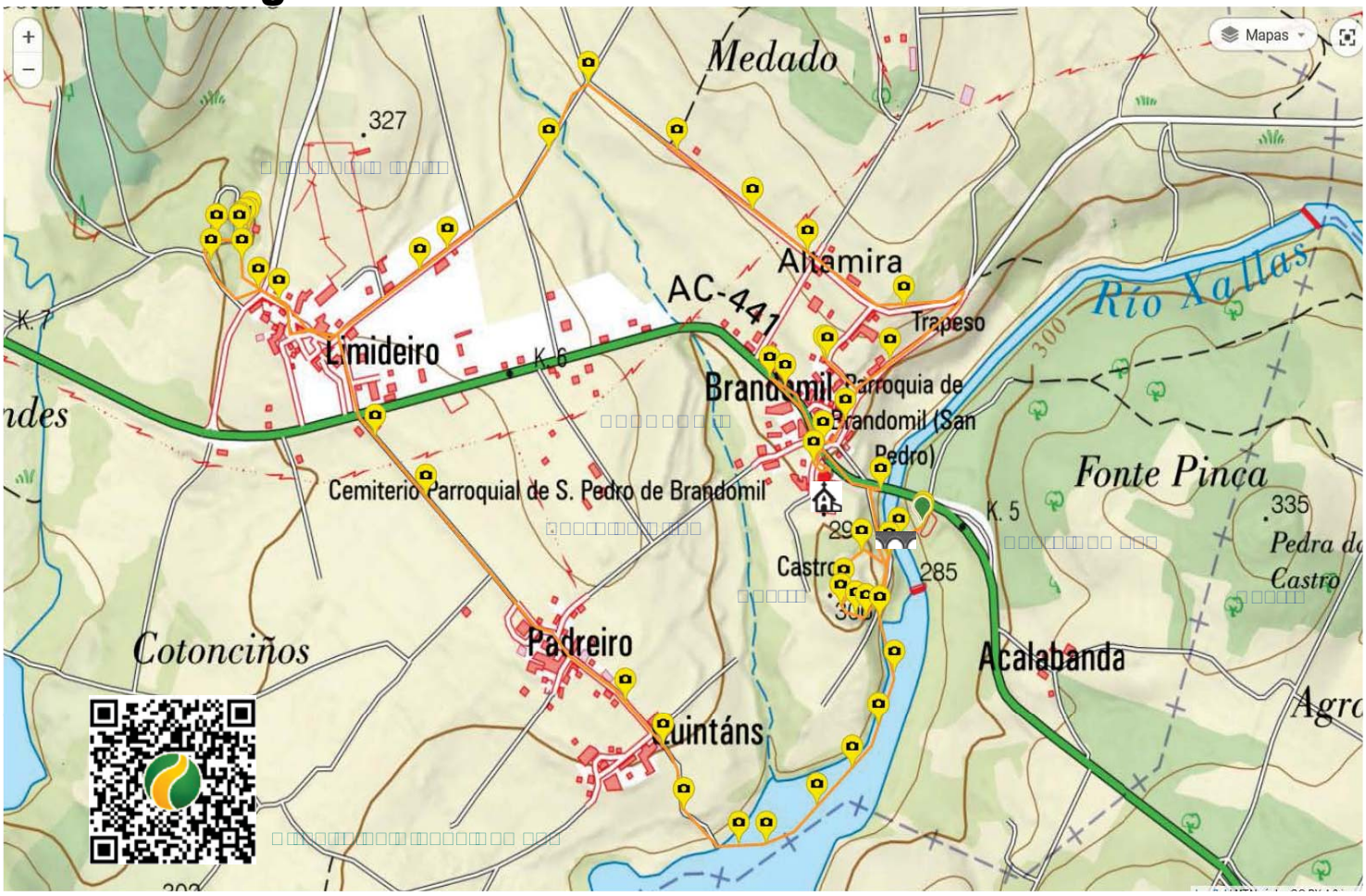

Ciudad Romana de Brandomil

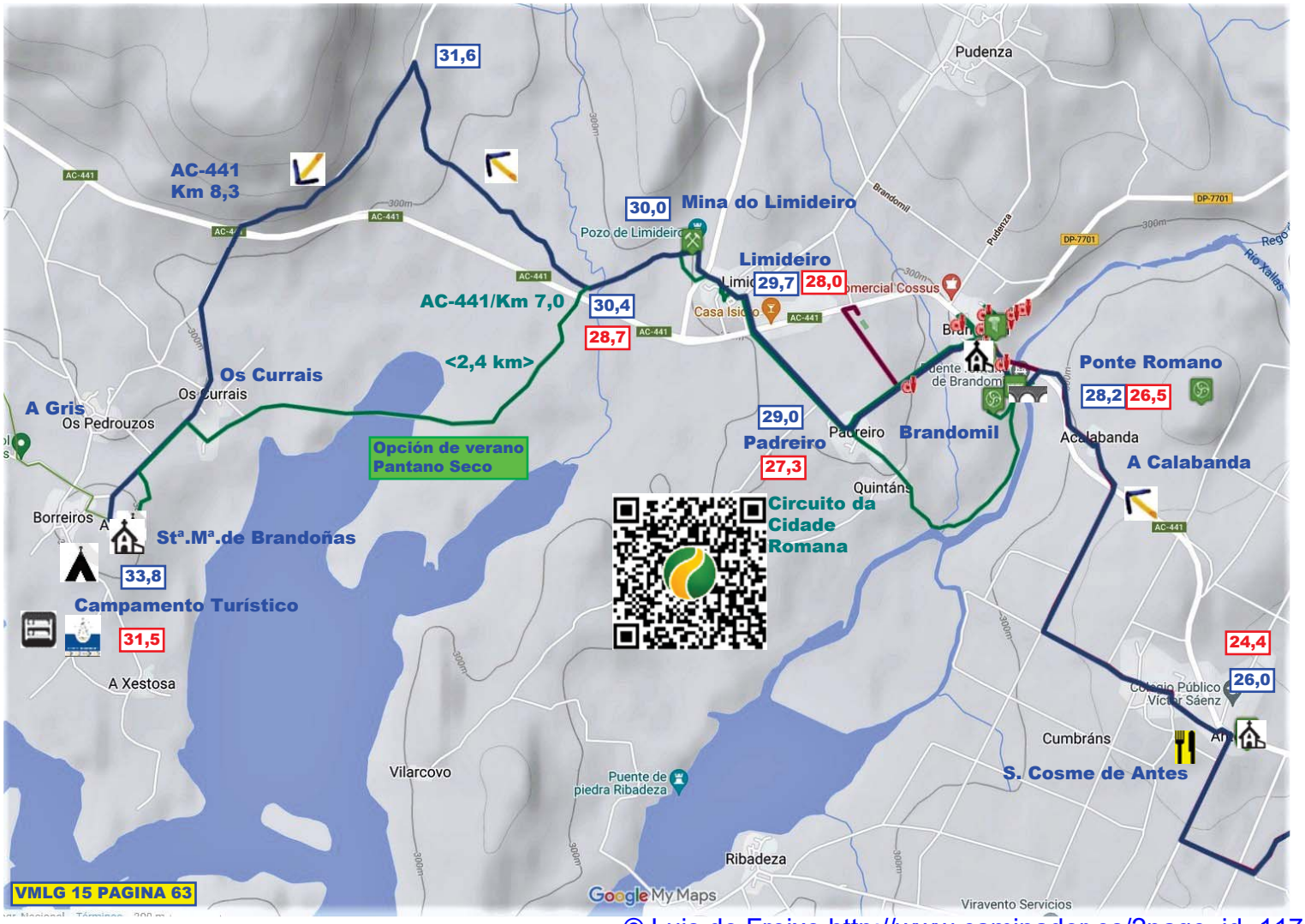

VMLG 15 PAGINA 63

© Luis do Freixo http://www.caminador.es/?page_id=117

VMLG.15: Negreira-A Baña-Stª Comba-Mazaricos-Zás

VMLG 15 PAGINA 62

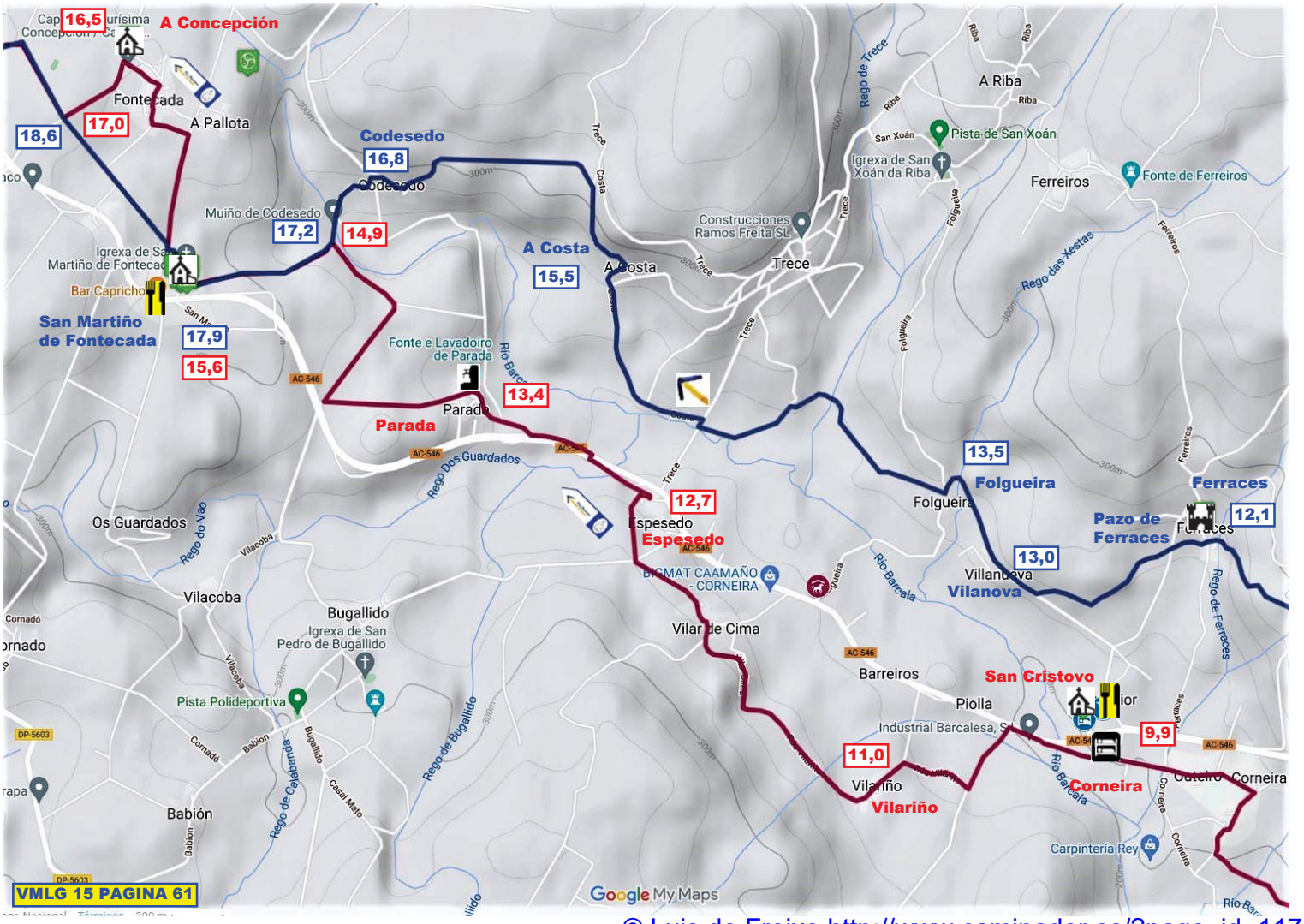

© Luis do Freixo http://www.caminador.es/?page_id=117

VMLG.15: Negreira-A Baña-Stª Comba-Mazaricos-Zás

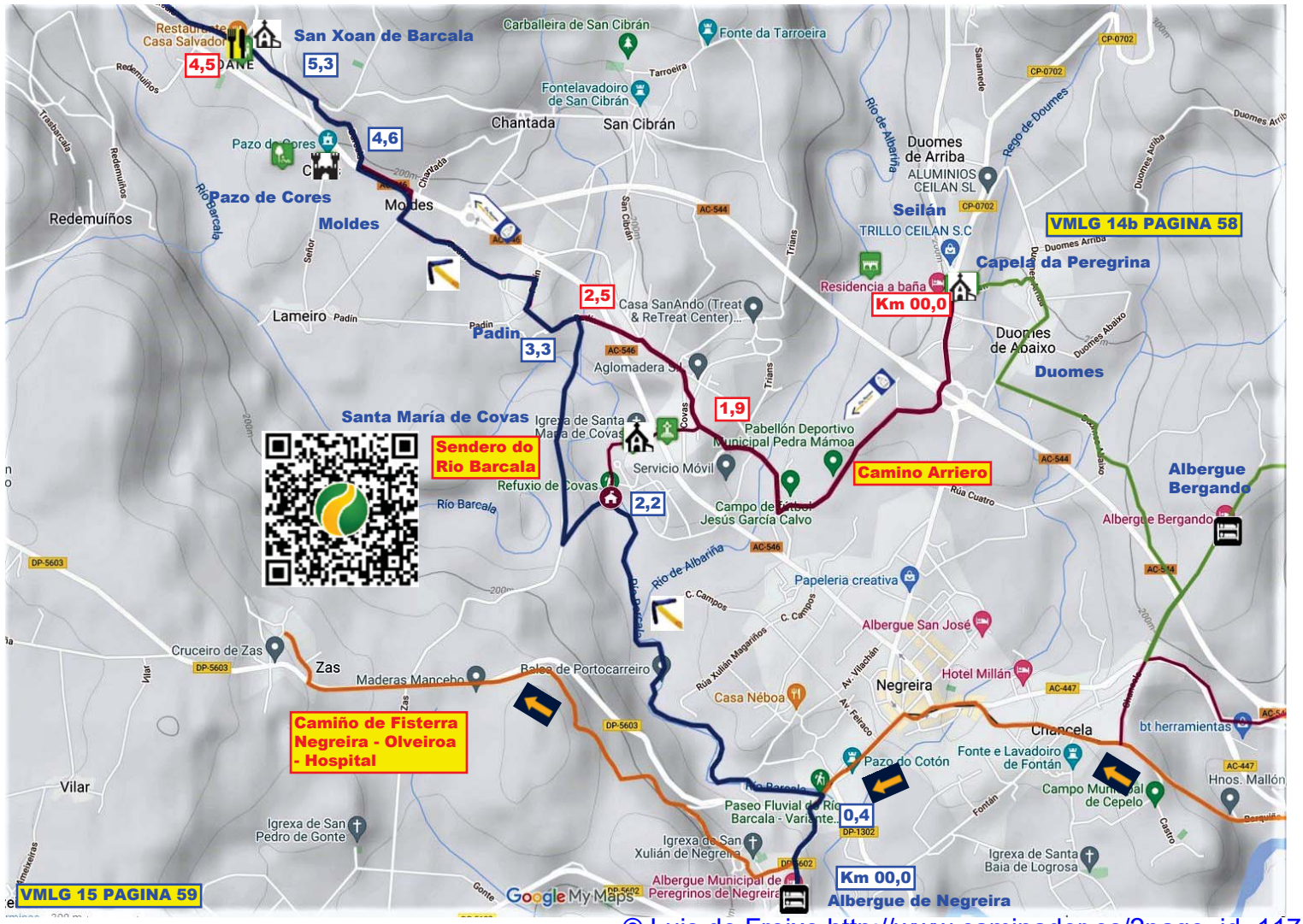

© Luis do Freixo http://www.caminador.es/?page_id=117